JAMHURI YA MUUNGANO WA TANZANIA

Tahadhari ya Hali mbaya ya Hewa na Hatua za Kuchukua

Toleo Na. 131 Limetolewa tarehe 16/05/2025 saa 8:59 mchana

OFISI YA WAZIRI MKUU
(SERA, BUNGE NA URATIBU)
IDARA YA MENEJIMENTI YA MAAFA
KITUO CHA OPERESHENI
NA MAWASILIANO YA DHARURA

SIKU YA 1, tarehe 16-05-2025

Mvua Kubwa

Mawimbi Makubwa

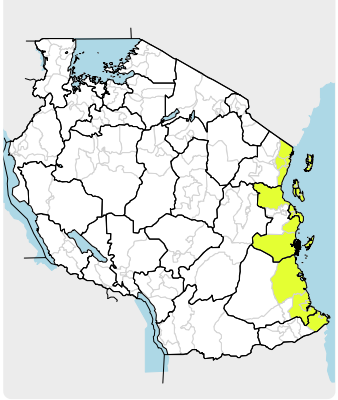

Upepo Mkali

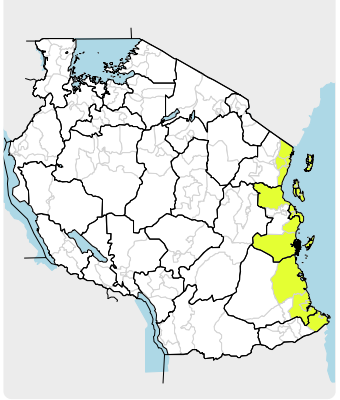

Mafuriko

Tathimini ya Kiwango cha Madhara yanayoweza kutokea na Hatua za Kuchukua

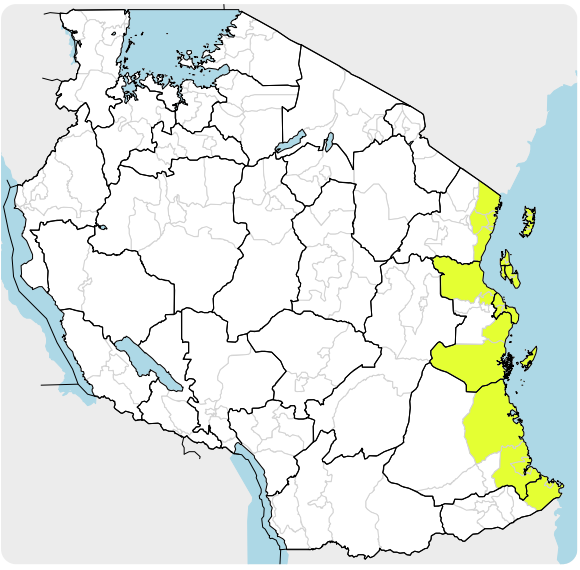

TAHADHARI KUBWA Hakuna

TAHADHARI Hakuna

ANGALIZO **Jamii inasisitizwa kuchukua hatua za tahadhari ikijumuisha:**

- Wavuvi na watumiaji wa bahari ya Hindi kuchukua tahadhari ya upepo mkali na mawimbi makubwa.
- Kuepuka kuvuka barabara na madaraja yaliyojaa maji.
- Watu wanaoishi maeneo ya mabondeni kuchukua tahadhari.
- Walimu na wazazi kuchukua tahadhari kwa wanafunzi wanaopita katika maeneo hatarishi.
- Makundi maalamu ikijumuisha watu wenye ulemavu, watoto na wazee wapatiwe taarifa ya tahadhari ya mapema na hatua stahiki zichukuliwe na jamii husika.
- Kuendelea kufuatilia taarifa za hali ya hewa zinazotolewa na Mamlaka ya Hali ya Hewa Tanzania.

Kamati za Usimamizi wa Maafa za Mikoa, Wilaya, Kata na Vijiji/Mitaa zinatakiwa kuchukua hatua stahiki za kujiandaa na kukabiliana na maafa ili kupunguza athari za majanga.

JAMHURI YA MUUNGANO WA TANZANIA

Tahadhari ya Hali mbaya ya Hewa na Hatua za Kuchukua

Toleo Na. 131 Limetolewa tarehe 16/05/2025 saa 8:59 mchana

OFISI YA WAZIRI MKUU
(SERA, BUNGE NA URATIBU)
IDARA YA MENEJIMENTI YA MAAFA
KITUO CHA OPERESHENI
NA MAWASILIANO YA DHARURA

Uchambuzi wa Majanga na Madhara yanayotarajiwa siku ya 1 tarehe 16-05-2025

Uchambuzi wa kitaalam kutoka Mamlaka ya Hali ya Hewa Tanzania

ANGALIZO la upepo mkali unaofikia kilomita 40 kwa saa limetolewa kwa baadhi ya maeneo ya ukanda wote wa pwani ya bahari ya Hindi (mikoa ya Tanga, Dar es Salaam, Pwani (ikijumuisha visiwa vya Mafia), Lindi na Mtwara pamoja na visiwa vya Unguja na Pemba).

UWEZEKANO WA KUTOKEA: WASTANI
KIWANGO CHA ATHARI ZINAZOWEZA KUTOKEA: WASTANI

Uchambuzi wa kitaalam kutoka Wizara ya Maji

ANGALIZO la ongezeko la wingi wa maji katika mito, vijito na mabwabwa limetolewa kwa maeneo machache ya Bonde la Wami Ruvu (Dar es Salaam, Morogoro na Pwani)

Uwezekano wa Kutokea: WASTANI
Kiwango cha Athari zinazoweza Kutokea: WASTANI

Uchambuzi wa kitaalam kutoka Idara ya Menejimenti ya Maafa

Madhara yanayoweza kutokea:
- Uwezekano wa kuathirika kwa shughuli za uvuvi na usafirishaji katika bahari ya Hindi kutokana na upepo mkali na mawimbi makubwa.
-Uwezekano wa makazi kuzingirwa na maji.
- Uwezekano wa barabara kutopitika kutokana na mafuriko.
- Kuathirika kwa shughuli za kijamii na kiuchumi.

Uwezekano wa kutokea: WASTANI
Kiwango cha athari zinazoweza kutokea: WASTANI

JAMHURI YA MUUNGANO WA TANZANIA

Tahadhari ya Hali mbaya ya Hewa na Hatua za Kuchukua

Toleo Na. 131 Limetolewa tarehe 16/05/2025 saa 8:59 mchana

OFISI YA WAZIRI MKUU
(SERA, BUNGE NA URATIBU)
IDARA YA MENEJIMENTI YA MAAFA
KITUO CHA OPERESHENI
NA MAWASILIANO YA DHARURA

SIKU YA 2, tarehe 17-05-2025

Mvua Kubwa

Mawimbi Makubwa

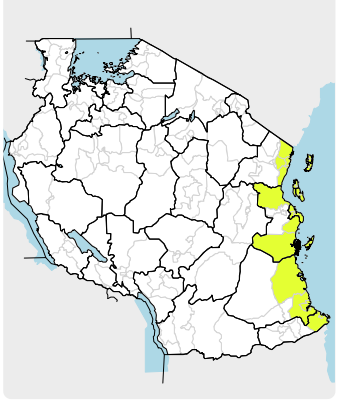

Upepo Mkali

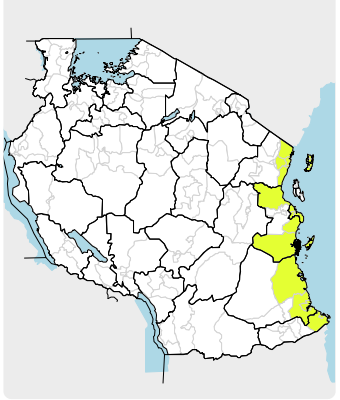

Mafuriko

Tathimini ya Kiwango cha Madhara yanayoweza kutokea na Hatua za Kuchukua

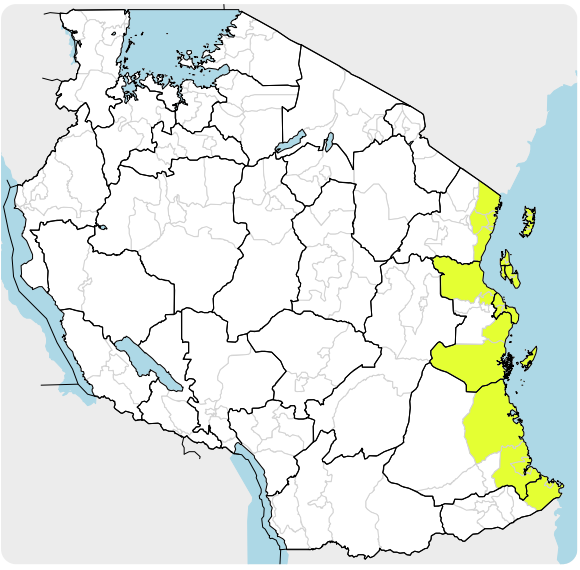

TAHADHARI KUBWA Hakuna

TAHADHARI Hakuna

ANGALIZO **Jamii inasisitizwa kuchukua hatua za tahadhari ikijumuisha:**

- Wavuvi na watumiaji wa bahari ya Hindi kuchukua tahadhari ya upepo mkali na mawimbi makubwa.
- Kuepuka kuvuka barabara na madaraja yaliyojaa maji.
- Watu wanaoishi maeneo ya mabondeni kuchukua tahadhari.
- Walimu na wazazi kuchukua tahadhari kwa wanafunzi wanaopita katika maeneo hatarishi.
- Makundi maalamu ikijumuisha watu wenye ulemavu, watoto na wazee wapatiwe taarifa ya tahadhari ya mapema na hatua stahiki zichukuliwe na jamii husika.
- Kuendelea kufuatilia taarifa za hali ya hewa zinazotolewa na Mamlaka ya Hali ya Hewa Tanzania.

Kamati za Usimamizi wa Maafa za Mikoa, Wilaya, Kata na Vijiji/Mitaa zinatakiwa kuchukua hatua stahiki za kujiandaa na kukabiliana na maafa ili kupunguza athari za majanga.

JAMHURI YA MUUNGANO WA TANZANIA

Tahadhari ya Hali mbaya ya Hewa na Hatua za Kuchukua

Toleo Na. 131 Limetolewa tarehe 16/05/2025 saa 8:59 mchana

OFISI YA WAZIRI MKUU
(SERA, BUNGE NA URATIBU)
IDARA YA MENEJIMENTI YA MAAFA
KITUO CHA OPERESHENI
NA MAWASILIANO YA DHARURA

Uchambuzi wa Majanga na Madhara yanayotarajiwa siku ya 2 tarehe 17-05-2025

Uchambuzi wa kitaalam kutoka Mamlaka ya Hali ya Hewa Tanzania

ANGALIZO la upepo mkali unaofikia kilomita 40 kwa saa limetolewa kwa baadhi ya maeneo ya ukanda wote wa pwani ya bahari ya Hindi (mikoa ya Tanga, Dar es Salaam, Pwani (ikijumuisha visiwa vya Mafia), Lindi na Mtwara pamoja na visiwa vya Unguja na Pemba).

UWEZEKANO WA KUTOKEA: WASTANI
KIWANGO CHA ATHARI ZINAZOWEZA KUTOKEA: WASTANI

Uchambuzi wa kitaalam kutoka Wizara ya Maji

ANGALIZO la ongezeko la wingi wa maji katika mito, vijito na mabwabwa limetolewa kwa maeneo machache ya Bonde la Wami Ruvu (Dar es Salaam, Morogoro na Pwani)

Uwezekano wa Kutokea: WASTANI
Kiwango cha Athari zinazoweza Kutokea: WASTANI

Uchambuzi wa kitaalam kutoka Idara ya Menejimenti ya Maafa

Madhara yanayoweza kutokea:

- Uwezekano wa kuathirika kwa shughuli za uvuvi na usafirishaji katika bahari ya Hindi kutokana na upepo mkali na mawimbi makubwa.
- Uwezekano wa makazi kuzingirwa na maji.
- Uwezekano wa barabara kutopitika kutokana na mafuriko.
- Kuathirika kwa shughuli za kijamii na kiuchumi.

Uwezekano wa kutokea: WASTANI
Kiwango cha athari zinazoweza kutokea: WASTANI

JAMHURI YA MUUNGANO WA TANZANIA

Tahadhari ya Hali mbaya ya Hewa na Hatua za Kuchukua

Toleo Na. 131 Limetolewa tarehe 16/05/2025 saa 8:59 mchana

OFISI YA WAZIRI MKUU
(SERA, BUNGE NA URATIBU)
IDARA YA MENEJIMENTI YA MAAFA
KITUO CHA OPERESHENI
NA MAWASILIANO YA DHARURA

SIKU YA 3, tarehe 18-05-2025

Mvua Kubwa

Mawimbi Makubwa

Upepo Mkali

Mafuriko

Tathimini ya Kiwango cha Madhara yanayoweza kutokea na Hatua za Kuchukua

TAHADHARI KUBWA Hakuna

TAHADHARI Hakuna

ANGALIZO **Jamii inasisitizwa kuchukua hatua za tahadhari ikijumuisha:**

- Watu watu wanaoishi maeneo ya mabondeni kuchukua hatua za tahadhari.
- Kuepuka kuvuka barabara na madaraja yaliyojaa maji.
- Walimu na wazazi kuchukua tahadhari kwa wanafunzi wanaopita katika maeneo hatarishi.
- Makundi maalamu ikijumuisha watu wenye ulemavu, watoto na wazee wapatiwe taarifa ya tahadhari ya mapema na hatua stahiki zichukuliwe na jamii husika.
- Kuendelea kufuatilia taarifa za hali ya hewa zinazotolewa na Mamlaka ya Hali ya Hewa Tanzania.

Kamati za Usimamizi wa Maafa za Mikoa, Wilaya, Kata na Vijiji/Mitaa zinatakiwa kuchukua hatua stahiki za kujiandaa na kukabiliana na maafa ili kupunguza athari za majanga.

Uchambuzi wa Majanga na Madhara yanayotarajiwa siku ya 3 tarehe 18-05-2025

Uchambuzi wa kitaalam kutoka Mamlaka ya Hali ya Hewa Tanzania

Uchambuzi wa kitaalam kutoka Wizara ya Maji

ANGALIZO la ongezeko la wingi wa maji katika mito, vijito na mabwabwa limetolewa kwa maeneo machache ya Bonde la Wami Ruvu (Dar es Salaam, Morogoro na Pwani)

Uwezekano wa Kutokea: WASTANI
Kiwango cha Athari zinazoweza Kutokea: WASTANI

Uchambuzi wa kitaalam kutoka Idara ya Menejimenti ya Maafa

Madhara yanayoweza kutokea:

- Baadhi ya makazi kuzingirwa na maji.
- Uwezekano wa barabara kutopitika kutokana na mafuriko.
- Kuathirika kwa shughuli za kijamii na kiuchumi.

Uwezekano wa kutokea: WASTANI
Kiwango cha athari zinazoweza kutokea: WASTANI

JAMHURI YA MUUNGANO WA TANZANIA

Tahadhari ya Hali mbaya ya Hewa na Hatua za Kuchukua

Toleo Na. 131 Limetolewa tarehe 16/05/2025 saa 8:59 mchana

OFISI YA WAZIRI MKUU
(SERA, BUNGE NA URATIBU)
IDARA YA MENEJIMENTI YA MAAFA
KITUO CHA OPERESHENI
NA MAWASILIANO YA DHARURA

Muhtasari wa Maeneo na kiwango cha madhara yanayotarajiwa siku ya 1

TAHADHARI KUBWA

TAHADHARI

ANGALIZO

Bagamoyo, Chake Chake, Ilala, Kaskazini A, Kaskazini B, Kati, Kibaha Urban, Kilwa, Kinondoni, Kusini, Lindi, Lindi Urban, Mafia, Magharibi, Micheweni, Mjini, Mkinga, Mkoani, Mkuranga, Mtwara, Mtwara Urban, Muheza, Pangani, Rufiji, Tanga Urban, Temeke, Wete

Muhtasari wa Maeneo na kiwango cha madhara yanayotarajiwa siku ya 2

TAHADHARI KUBWA

TAHADHARI

ANGALIZO

Bagamoyo, Chake Chake, Ilala, Kaskazini A, Kaskazini B, Kati, Kibaha Urban, Kilwa, Kinondoni, Kusini, Lindi, Lindi Urban, Mafia, Magharibi, Micheweni, Mkinga, Mkoani, Mkuranga, Mtwara, Mtwara Urban, Muheza, Pangani, Rufiji, Tanga Urban, Temeke, Wete

Muhtasari wa Maeneo na kiwango cha madhara yanayotarajiwa siku ya 3

TAHADHARI KUBWA

TAHADHARI

ANGALIZO

Ilala, Kinondoni, Temeke

Wasiliana nasi: 190 au eocctz@pmo.go.tz

Tahadhari ya Hali mbaya na Hatua za Kuchukua kwa kipindi cha siku tatu imetolewa na Kituo cha Operesheni na Mawasiliano ya Dharura, Idara ya Menejimenti ya Maafa, Ofisi ya Waziri Mkuu kwa kushirikiana na Mamlaka ya Hali ya Hewa Tanzania na Wizara ya Maji

Ministero degli Affari Esteri e della Cooperazione Internazionale

ITALIAN AGENCY FOR DEVELOPMENT COOPERATION

UNDRR UN Office for Disaster Risk Reduction

cima RESEARCH FOUNDATION